TOUR NATURALISTICO

TOUR NATURALISTICO-SPORTIVO: COMO, VARESE, TICINO

GIORNO 1 – COMO: LAGO, TREKKING E PANORAMI

stazione san giovanni - lungolago viale geno - funicolare como

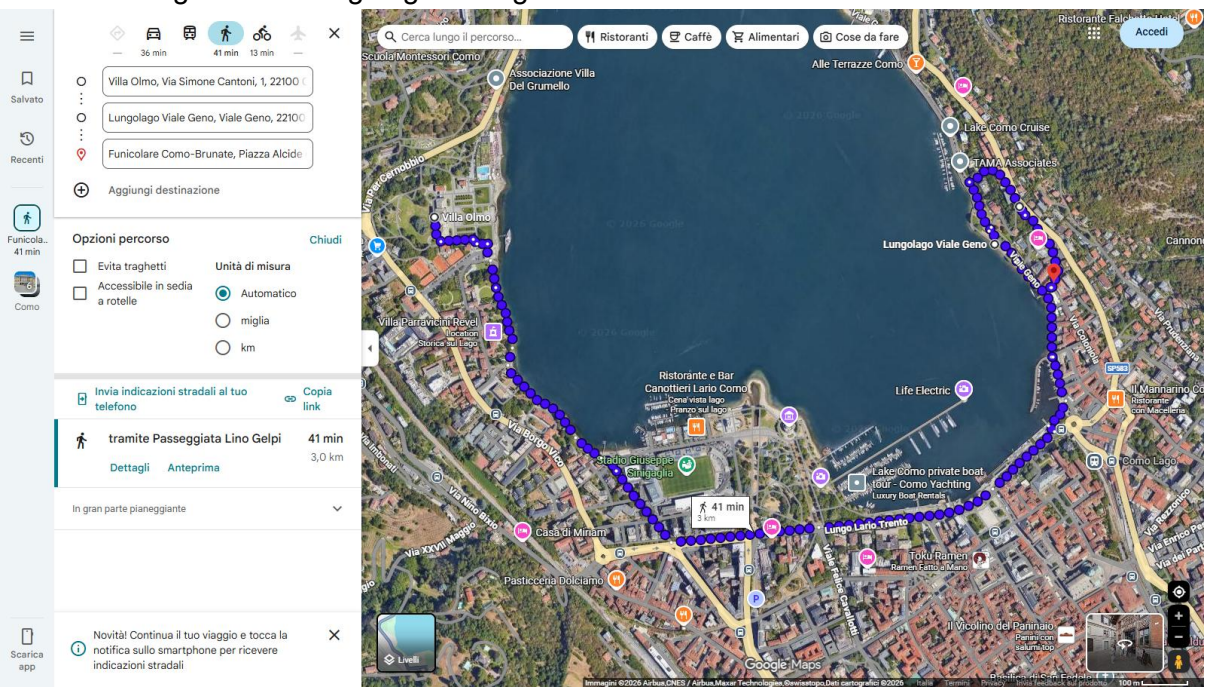

funicolare como - parco spina verde

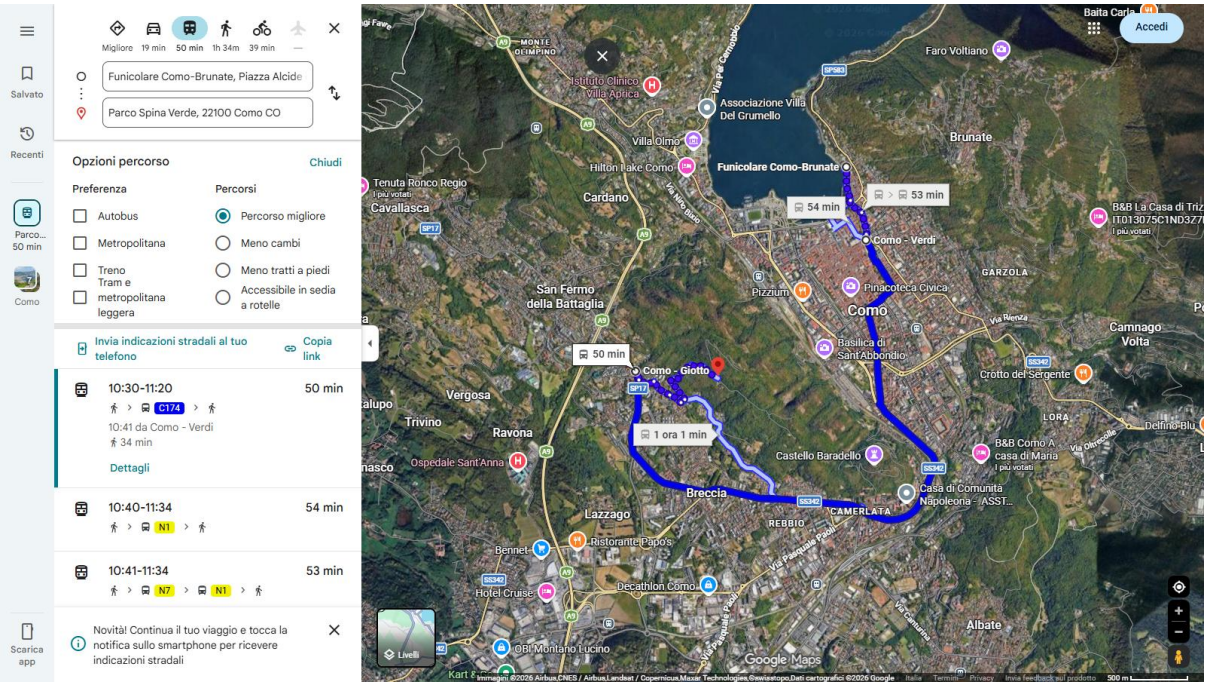

parco spina verde - croce di sant’eutichio

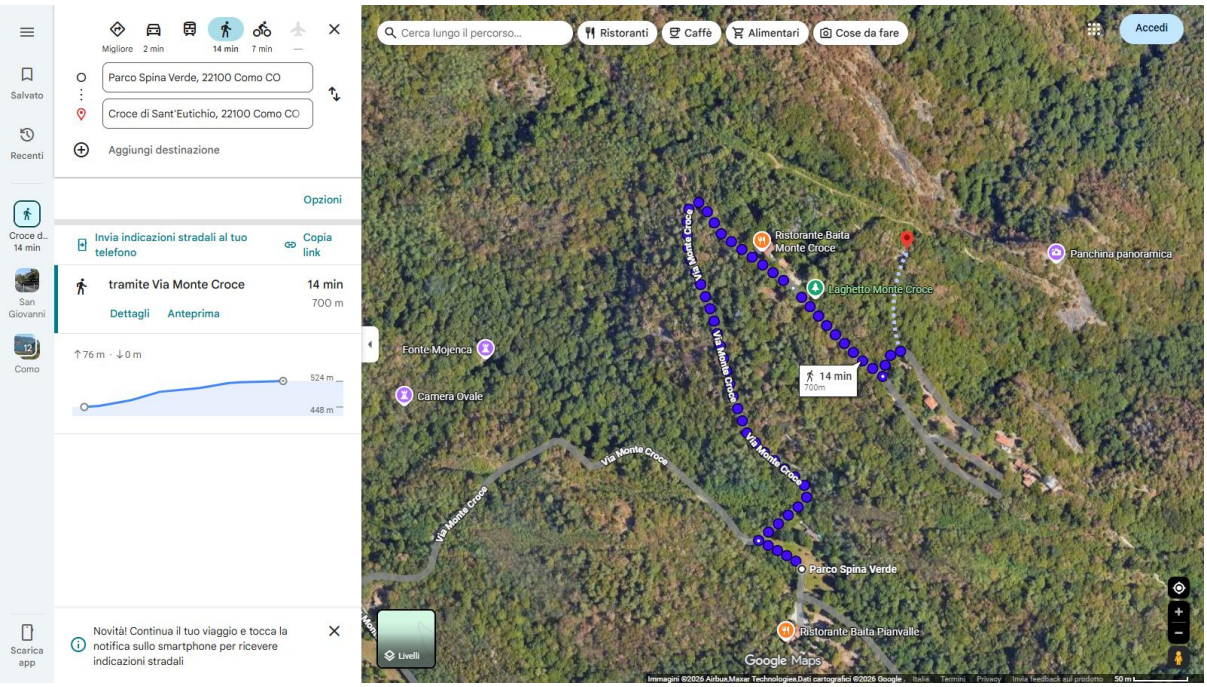

croce di sant’eutichio - panchina panoramica

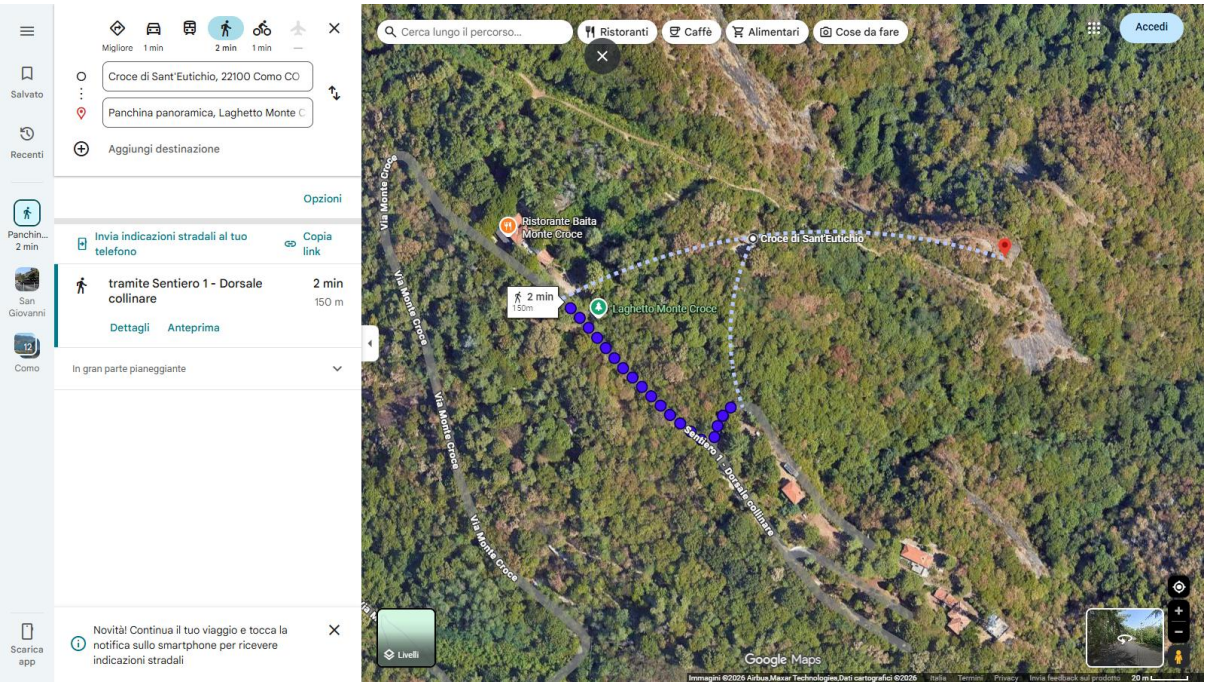

panchina panoramica - belvedere baita elisa

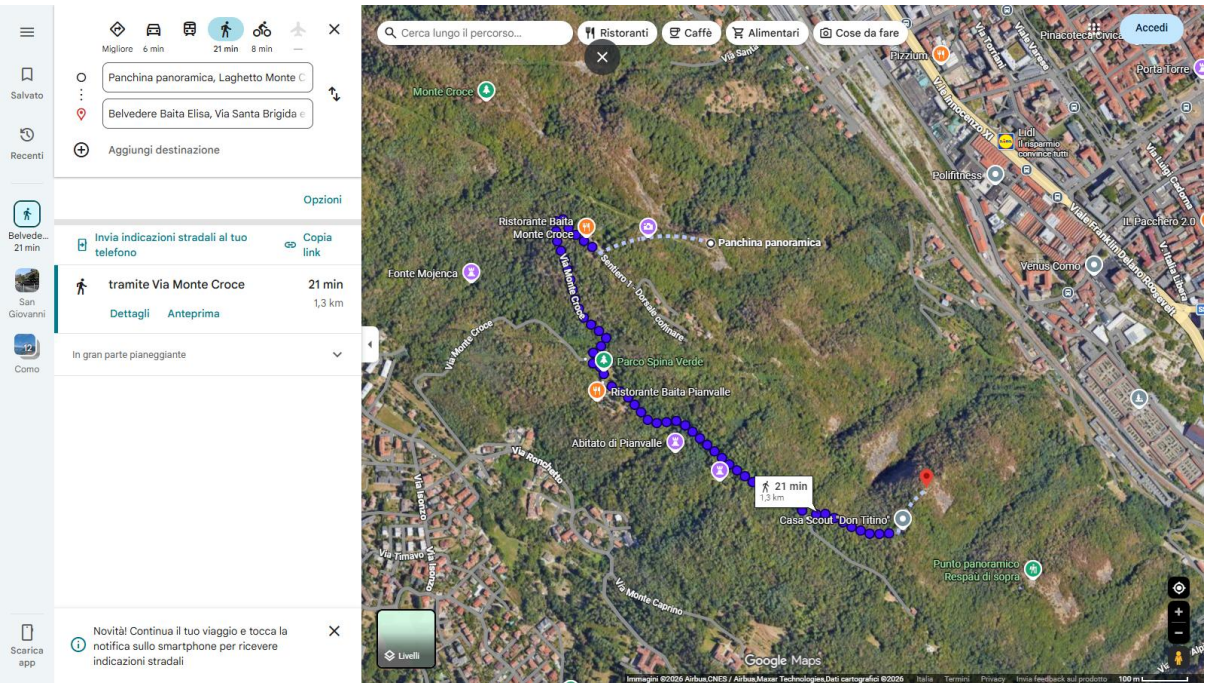

panchina panoramica - stazione san giovanni

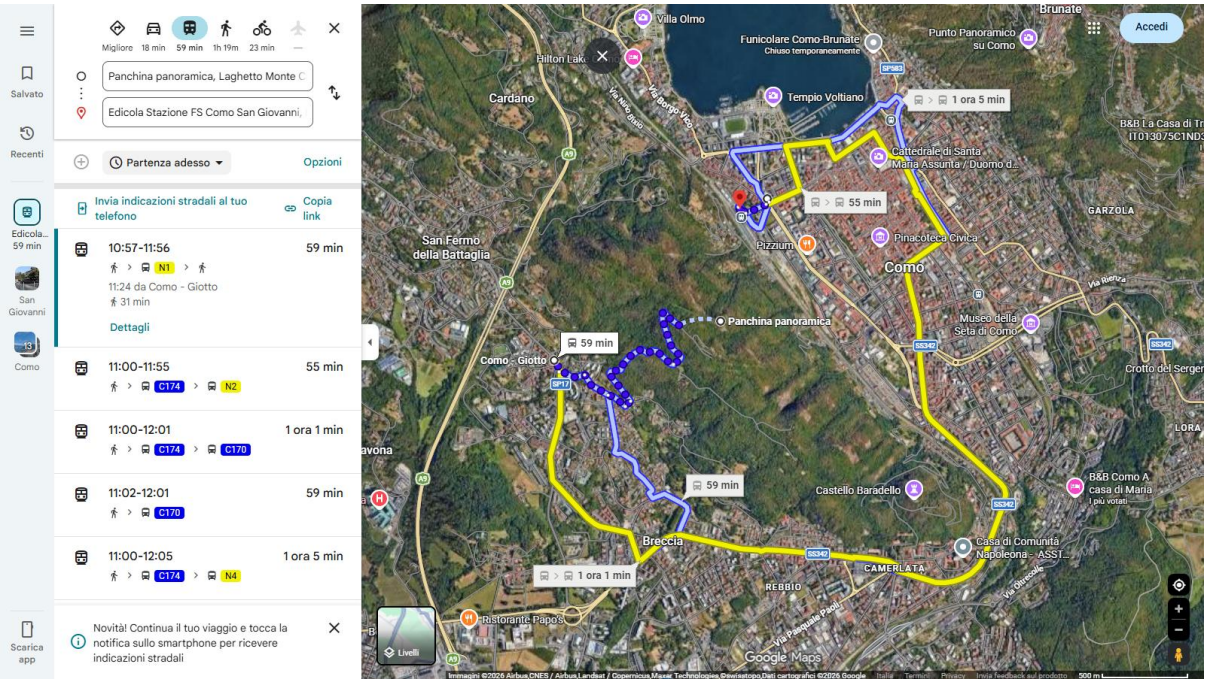

GIORNO 2 – VARESE: SACRO MONTE E CAMMINATE NATURALI

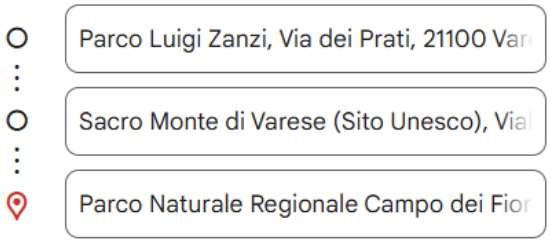

1. Sacro Monte di Varese

- **Tipo attività:** trekking storico-naturalistico
- **Lunghezza:** circa 5 km A/R, dislivello 200 m
- **Durata:** 2 ore camminata continua
- **Accesso:** gratuito, sempre aperto
- **Descrizione:** percorso tra 14 cappelle con statue e affreschi, patrimonio UNESCO, panorama sulla città e sulle Prealpi.
- **Come arrivare da Como:**

    - Treno: Como San Giovanni → Varese FS (~1h, treni ogni ora, prezzo indicativo €6,40 2ª classe)

- **Trasferimento dalla stazione Varese FS:**
    - **Bus urbano linea C**, piazzale stazione → Prima Cappella, frequenza 15-20 min
    - Tempo a piedi stimato: **40–50 min in salita** → meglio bus per ridurre camminata lunga

---

2. Parco Regionale Campo dei Fiori

- **Tipo attività:** trekking medio, corsa in montagna, osservazione natura
- **Durata:** 2–4 ore, diversi sentieri CAI segnati
- **Accesso:** gratuito
- **Descrizione:** foreste, prati, fauna locale, panorami sulle Alpi e sul Lago di Varese
- **Come arrivare:**
    - Dalla Prima Cappella: **bus urbano verso fermata Schianno/Velate**, 15-20 min → evita 30-50 min a piedi su sentieri in salita
    - Accesso anche dal centro di Varese tramite bus urbano

---

3. Lago di Varese – Parco Luigi Zanzi (Schiranna)

- **Tipo attività:** corsa, camminata, ciclismo
- **Lunghezza anello:** circa 3 km pianeggiante
- **Accesso:** gratuito, sempre aperto

- **Come arrivare:**
    - Dal centro di Varese o Campo dei Fiori: **bus urbano linea Schiranna**, frequenza 30 min, tempo 20 min
    - A piedi: circa 50–60 min pianeggianti

GIORNO 3 – SPORT D'ACQUA E TREKKING LEGGERO (VARESE)

1. Canottaggio Lago di Varese (Schiranna)

- **Attività visibile:** canottaggio, sport acquatici
- **Orari allenamenti:** 6:30–9:00 e 17:00–19:00, osservabile gratuitamente
- **Accesso:** pubblico

2. Trekking leggero – Giardini Estensi

- **Tipo attività:** passeggiata, jogging, esplorazione naturalistica
- **Durata:** 1–2 ore
- **Accesso:** gratuito
- **Descrizione:** giardini storici con fontane, sculture, alberi secolari
- **Come arrivare:** a piedi dal centro, oppure bus urbano

3. Sacro Monte + Campo dei Fiori (opzionale)

- **Tipo attività:** trekking medio, sportivo

- **Durata:** 2–4 ore

- **Accesso:** gratuito
- **Descrizione:** salite panoramiche, vista sulle Alpi, natura incontaminata

---

GIORNO 4 – TICINO, BELLINZONA E LUGANO (SVIZZERA) – TREKKING E PANORAMI

1. Trasporti: Varese → Bellinzona

- **Treno:** Varese FS → Mendrisio → Bellinzona

- **Durata:** circa 1h45–2h

- **Frequenza:** treni ogni ora

- **Prezzo:** circa €16–20 (combinazione Trenord + TILO)

---

2. Castelli di Bellinzona

- **Tipo attività:** trekking urbano, visita storica, camminate su mura

- **Orari:** Apr–Ott: 10:00–18:00 / Nov–Mar: 10:30–16:00

- **Prezzo:** pass 3 castelli CHF 28

- **Accesso:** scale e camminamenti aperti, trekking leggero tra castelli

Come arrivare:

- Dalla stazione: Castelgrande 10 min a piedi, Montebello e Sasso Corbaro tramite sentieri segnalati o bus locali

---

3. Monte San Salvatore (vicino Lugano)

- **Tipo attività:** trekking panoramico, camminata sportiva, paesaggi
- **Accesso:** funicolare da Paradiso
- **Orari:** 9:00–17:00 (stagionale)
- **Prezzo A/R:** CHF 32
- **Sentieri:** multipli percorsi trekking in cima, discese a piedi possibili

Come arrivare:

- `Treno Bellinzona → Lugano (~30 min)`
- Poi bus locale o funicolare Paradiso

---

4. Lungolago di Lugano

- **Tipo attività:** corsa, camminata, ciclismo
- **Accesso:** gratuito, sempre aperto
- **Descrizione:** percorso pianeggiante con vista lago e montagne, ideale per defaticamento o jogging leggero

Società Canottieri Varese A.S.D, Via dei C

Giardini e Palazzo Estensi, Via Luigi Sacc

Sacro Monte di Varese (Sito Unesco), Via

Lungolago di Lugano, 6900 Lugano, Sviz